المدرسة الوطنية العليا للذكاء الاصطناعي وعلوم المعطيات - تارودانت
ⵜⴰⵙⴷⴰⵡⵉⵜ ⵜⴰⵏⴰⵎⵓⵔⵜ ⵜⴰⵏⴰⵅⵉⵍⵉⵏⵜ ⵏ ⵓⵏⵎⵓⵙⵙⴰⵏ ⴰⵏⴰⴼⵍⵍⴰ ⴷ ⵜⵎⴰⵙⵙⴰⵏⵉⵏ ⵏ ⵜⵓⵙⵙⴰⵏⵜ - ⵜⴰⵔⵓⴷⴰⵏⵜ
ECOLE NATIONALE SUPÉRIEURE DE L'INTELLIGENCE ARTIFICIELLE ET SCIENCES DES DONNÉES – TAROUDANT

Filière : Ingénierie des Technologies et Confiance Numérique (SITCN)

Rapport d'Audit et de Sécurisation

Sujet

Agadir Tsunami-Ready

(Gestion des routes d'évacuation et des sirènes d'alerte)

Rôle

Blue Team (Configuration et Défense)

Réalisé par : ABELLAH M'RAK
IKRAM MOURABIT

Encadré par : Pr. SARA EL-ATEIF

Module : Systèmes d'Information et Bases de Données (SIBD)

Soutenu le : 14/04/20

Année Universitaire : 2024/2026

TABLE DES MATIÈRES

1. Objectif de ce rapport 2
2. Niveau de criticité 2
3. Structure du projet 2
I. Analyse des Risques : 4
1. Modèle de Menaces : 4
2. Surface d'Attaque : 4
3. Analyse des Risques (Méthode DREAD) : 4
II. Vulnérabilités Détectées (Pre-Fix) 5
1. V-01 : SQL Injection 5
2. V-02 : Man-in-the-Middle (MITM) 5
3. V-03 : Absence de Contrôle d'Accès (RBAC) 6
4. V-04 : Déni de Service (DoS) : 6
5. V-05 : Falsification des Signaux d'Alerte : 6
6. V-06 : Données Capteurs Aberrantes 6
III. Architecture Sécurisée Proposée : 7
1. Architecture Globale Sécurisée : 7
2. Implémentation RBAC Complète : 7
3. Protection Anti-SQL Injection : 9
4. Sécurisation des Communications (HTTPS/TLS) : 10
5. Signature HMAC des Signaux d'Alerte : 11
6. Trigger SQL – Déclenchement Sécurisé des Sirènes : 12
7. Protection Firewall (UFW) 13
IV. Chiffrement des Données Sensibles : 14

Introduction

Le système Agadir Tsunami-Ready est un système d'information critique conçu pour la région Souss-Massa. Il assure la gestion des routes d'évacuation côtières et le déclenchement automatique des sirènes d'alerte en cas de détection d'un séisme marin de magnitude supérieure ou égale à 6,5 sur l'échelle de Richter.

1. Objectif de ce rapport

Ce document constitue le rapport d'audit de sécurité produit par la Blue Team. Il couvre l'analyse des risques, les vulnérabilités identifiées dans le projet Django existant, les solutions de défense proposées, et les mesures concrètes mises en œuvre pour sécuriser l'application.

2. Niveau de criticité

Le système est classé de niveau A — criticité maximale — pour trois raisons fondamentales :

- Temps de réponse imposé : inférieur à 1 seconde pour toute alerte critique.
- Fiabilité absolue : toute alerte manquée ou falsifiée constitue un risque direct pour des vies humaines.
- Disponibilité 24h/24, 7j/7, 365 jours par an, sans exception, y compris en période de crise.

3. Structure du projet

Le projet est développé avec le framework Django (Python). L'arborescence analysée est la suivante :

```
Tsunami-Ready (22)/
├── Architects/
│   ├── .venv/
│   ├── admin_dashboard/
│   ├── alertes/
│   ├── cartes/
│   ├── config/
│   ├── evacuation/
│   ├── sql/
│   ├── utilisateurs/
│   ├── .env
│   ├── check_django_import.py
│   ├── check_import2.py
│   ├── environment.yml
│   ├── manage.py
│   ├── nginx.conf
│   ├── README.md
│   └── ufw_setup.sh
├── Augmenteds_team/
│   ├── membre2-alerts/
│   │   ├── node_modules/
│   │   ├── .env
│   │   ├── localhost+1-key.pem
│   │   ├── localhost+1.pem
│   │   ├── node_out.txt
│   │   ├── node_server_log.txt
│   │   ├── package-lock.json
│   │   ├── package.json
│   │   └── server.js
│   ├── node_modules/
```

```
│   ├── src/
│   │   ├── components/
│   │   │   ├── app.js
│   │   │   ├── assembly.js
│   │   │   ├── charts.js
│   │   │   ├── dashboard.js
│   │   │   ├── map.js
│   │   │   └── sirens.js
│   │   ├── services/
│   │   │   ├── api.js
│   │   │   ├── auth.js
│   │   │   └── websocket.js
│   │   ├── store/
│   │   │   └── state.js
│   │   ├── styles/
│   │   │   └── main.css
│   │   └── utils/
│   │       └── evacuation.js
│   ├── .gitignore
│   ├── app.py
│   ├── events_import.json
│   ├── index.html
│   ├── login.html
│   ├── package-lock.json
│   ├── package.json
│   ├── README.md
│   ├── requirements.txt
│   ├── teste.sql
│   └── tsunami_ready.sql
├── .gitignore
├── SETUP_GUIDE.pdf
└── start_tsunami_ready.bat
```

Figure 1 : Structure arborescente du projet Django (avant sécurisation

I. Analyse des Risques :

1. Modèle de Menaces :

Le système est exposé à des adversaires externes qui cherchent à provoquer de fausses alertes, empêcher de vraies alertes ou voler des données sensibles, ainsi qu'à des adversaires internes pouvant exploiter des privilèges excessifs pour modifier des paramètres critiques.

2. Surface d'Attaque :

L'API REST, exposée directement sur Internet et responsable des routes GPS et du déclenchement des sirènes, représente un risque critique. Le dashboard web présente un risque élevé en raison de son exposition publique. La base de données PostgreSQL, bien que située en réseau interne, reste à risque élevé en cas de compromission interne. Les capteurs sismiques, connectés à un réseau externe, constituent également un point critique, tout comme le système de sirènes connecté au réseau local, dont une compromission aurait des conséquences graves.

3. Analyse des Risques (Méthode DREAD) :

La falsification des signaux d'alerte et les injections SQL présentent les niveaux de risque les plus élevés avec un score de 8.4, en raison de leur impact direct sur la sécurité des populations. Les attaques par déni de service suivent avec un score de 8.2, menaçant la disponibilité du système en situation critique. L'accès non autorisé aux sirènes et l'injection de données capteurs atteignent respectivement des scores de 7.0 et 7.2. Enfin, les attaques de type Man-in-the-Middle, bien que sérieuses, présentent un score légèrement inférieur de 6.8.

II. Vulnérabilités Détectées (Pre-Fix)

Les vulnérabilités suivantes ont été identifiées lors de l'analyse du code source du projet Django. Elles représentent l'état du système avant application des mesures de sécurité.

1. V-01 : SQL Injection

- **Description :** Les paramètres de l'API (coordonnées GPS, identifiant de zone, magnitude) sont concaténés directement dans les requêtes SQL sans validation ni paramétrage. Un attaquant peut manipuler ces paramètres pour lire, modifier ou supprimer les données de la base.
- **Exemple d'exploitation :**

```
Augmenteds_team > teste.sql > ...
1  GET /api/route?zone_id=' OR '1'='1' --
2  → Retourne TOUTES les zones (contournement de filtre géographique)
3
4  POST /api/siren/activate
5  Body: {"magnitude": "6.5; DROP TABLE evacuation_routes; --"}
6  → Destruction de la table des routes d evacuation (injection SQL)
```

Figure 2 : Exemple d'exploitation d'une injection SQL dans l'API

- **Impact potentiel :** Manipulation des routes d'évacuation affichées aux citoyens, suppression de données critiques, contournement des contrôles d'accès.

2. V-02 : Man-in-the-Middle (MITM)

- **Description :** Les communications entre le dashboard et l'API, ainsi qu'entre l'API et les capteurs sismiques, transitent en HTTP non chiffré. Un attaquant positionné sur le réseau peut intercepter et modifier ces communications, notamment les signaux d'activation des sirènes.
- **Scénario d'attaque :** Un attaquant avec accès au réseau local (ou via un point d'accès WiFi compromis) intercepte la réponse du capteur sismique indiquant magnitude=7.2 et la remplace par magnitude=5.0, empêchant ainsi le déclenchement des sirènes.

3. V-03 : Absence de Contrôle d'Accès (RBAC)

- **Description :** Le système ne dispose d'aucune gestion des rôles. Tout utilisateur authentifié (ou même non authentifié sur certains endpoints) peut déclencher les sirènes, modifier les routes d'évacuation ou accéder aux logs système.
- **Endpoints non protégés :**
  - **POST /api/siren/activate** → Aucune vérification de rôle
  - **PUT /api/routes/{id}** → Modifiable par tout utilisateur
  - **GET /api/admin/logs** → Logs accessibles publiquement
  - **DELETE /api/zones/{id}** → Suppression sans autorisation

4. V-04 : Déni de Service (DoS) :

- **Description :** Aucune limitation du débit de requêtes (rate limiting) n'est en place. Lors d'une alerte réelle, des milliers de citoyens accèdent simultanément au système, pouvant le rendre indisponible précisément au moment critique.
- **Impact :** Le dashboard ne répond plus, les routes d'évacuation ne peuvent plus être consultées, le délai de réponse < 1s est violé.

5. V-05 : Falsification des Signaux d'Alerte :

- **Description :** Les signaux envoyés par les capteurs sismiques à l'API ne sont pas signés numériquement. N'importe quel client peut envoyer une requête forgée avec une magnitude arbitraire.

6. V-06 : Données Capteurs Aberrantes

- **Description :** Le système n'effectue aucune validation des données entrantes des capteurs. Un capteur défaillant ou compromis peut envoyer des valeurs impossibles (magnitude négative, coordonnées hors zone) qui corrompent la prise de décision.
- **Exemples de données aberrantes acceptées :**
  - **{"magnitude": -3.5}** → Alerte non déclenchée (normal)
  - **{"magnitude": 99.9}** → Déclenchement multiple en cascade
  - **{"latitude": 999.999}** → Calcul GPS corrompu

III. Architecture Sécurisée Proposée :

1. Architecture Globale Sécurisée :

L'architecture applique le principe de défense en profondeur. Chaque couche dispose de ses propres mécanismes de sécurité indépendants. La compromission d'une couche ne suffit pas à compromettre l'ensemble du système.

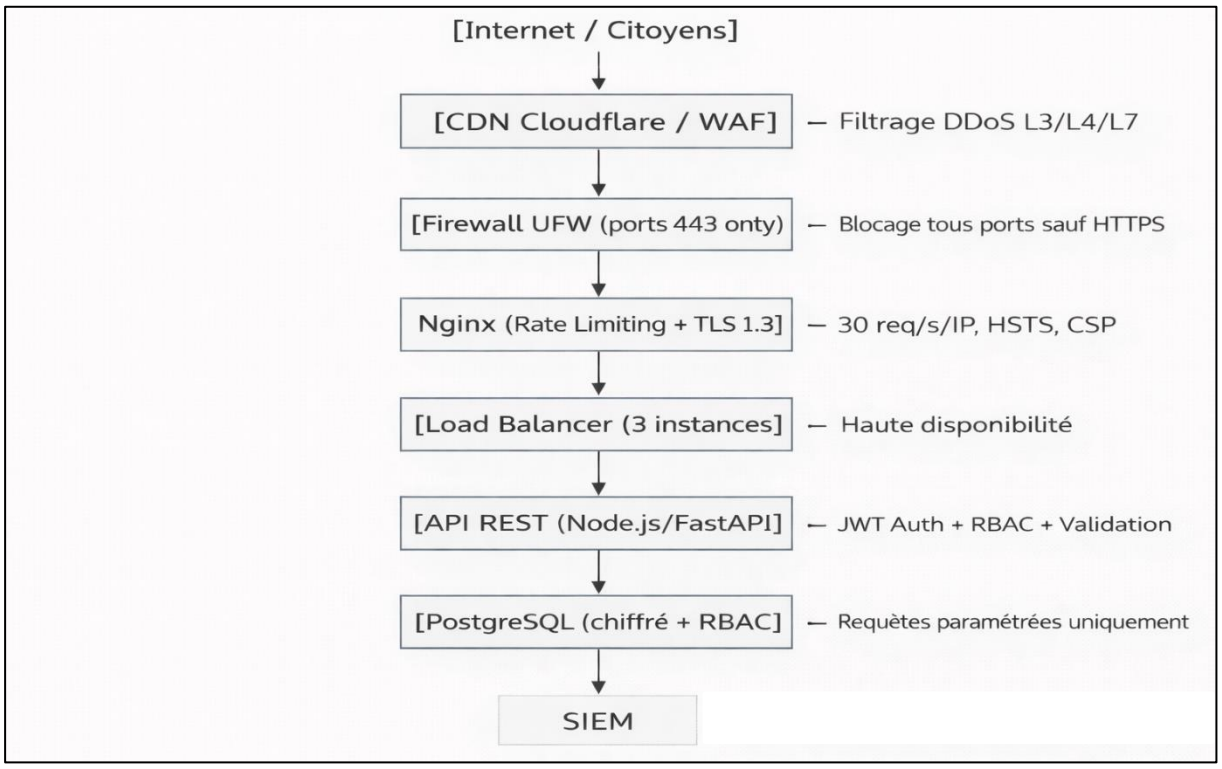

Figure 3 : Architecture sécurisée proposée – défense en profondeur

2. Implémentation RBAC Complète :

- **utilisateurs/models.py**
  - **Avant :**

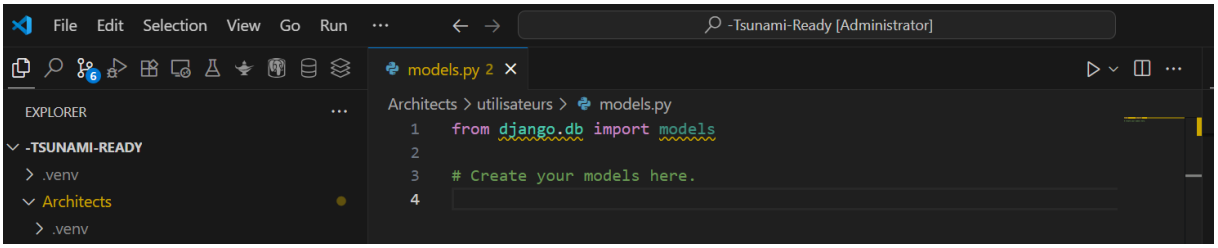

Figure 4 : Modèle User avant l'ajout du champ role (RBAC)

➢ **Après :**

```python
from django.db import models
from django.contrib.auth.models import AbstractUser

class User(AbstractUser):
    ROLE_CHOICES = [
        ('admin',    'Administrateur'),
        ('operator', 'Opérateur'),
        ('citizen',  'Citoyen'),
    ]
    role = models.CharField(max_length=20, choices=ROLE_CHOICES, default='citizen')
```

Figure 5 : Modèle User après intégration des rôles (RBAC)

- **config/settings.py**

➢ **Avant :**

```python
# Quick-start development settings - unsuitable for production
# See https://docs.djangoproject.com/en/5.2/howto/deployment/checklist/

# SECURITY WARNING: keep the secret key used in production secret!
SECRET_KEY = "django-insecure-1g3ptfe=mj70x%_@aca+wihnls@(^s)(v-bj)o3^k8_mb$g+1-"

# SECURITY WARNING: don't run with debug turned on in production!
DEBUG = True

ALLOWED_HOSTS = []
```

Figure 6 : Fichier settings.py avant externalisation des secrets

➢ **Après :**

```python
from decouple import config

# Clé secrète chargée depuis .env
SECRET_KEY = config('SECRET_KEY')

# Debug désactivé en production
DEBUG = config('DEBUG', default=False, cast=bool)

# Hôtes autorisés explicitement
ALLOWED_HOSTS = ['tsunami.souss-massa.ma', '127.0.0.1']

# — Sécurité HTTPS ————————————————
SECURE_SSL_REDIRECT            = True
SECURE_HSTS_SECONDS            = 31536000
SECURE_HSTS_INCLUDE_SUBDOMAINS = True
SECURE_HSTS_PRELOAD            = True

# — Cookies sécurisés ————————————————
SESSION_COOKIE_SECURE   = True
CSRF_COOKIE_SECURE      = True
SESSION_COOKIE_HTTPONLY = True

# — Headers de sécurité ————————————————
SECURE_CONTENT_TYPE_NOSNIFF = True
X_FRAME_OPTIONS             = 'DENY'

# — Application RBAC ————————————————
AUTH_USER_MODEL = 'utilisateurs.User'
```

Figure 7 : Fichier settings.py après

- **utilisateurs/views.py**
  - **Avant :**

```
from django.shortcuts import render

# Create your views here.
```

Figure 8 : Vue Django avant l'implémentation du contrôle d'accès

  - **Après :**

```
from functools import wraps
from django.http import JsonResponse
from django.contrib.auth.decorators import login_required

def require_role(*allowed_roles):
    """Décorateur : vérifie que l'utilisateur a le bon rôle."""
    def decorator(view_func):
        @wraps(view_func)
        @login_required
        def wrapper(request, *args, **kwargs):
            if request.user.role not in allowed_roles:
                return JsonResponse({'error': 'Permission insuffisante'}, status=403
            return view_func(request, *args, **kwargs)
        return wrapper
    return decorator
```

Figure 9 : Vue Django avec décorateurs @login_required et vérification de rôle

3. Protection Anti-SQL Injection :

- **evacuation/views.py**
  - **Avant :**

```
from django.shortcuts import render

# Create your views here.
```

Figure 10 : Code vulnérable à l'injection SQL (concaténation directe)

➢ **Après :**

```python
from django.http import JsonResponse
from utilisateurs.views import require_role

BOUNDS = { 'lat': (29.0, 31.5), 'lon': (-10.0, -7.5) }

def validate_gps(lat, lon):
    if not (BOUNDS['lat'][0] <= lat <= BOUNDS['lat'][1]):
        raise ValueError(f'Latitude invalide: {lat}')
    if not (BOUNDS['lon'][0] <= lon <= BOUNDS['lon'][1]):
        raise ValueError(f'Longitude invalide: {lon}')

@require_role('admin', 'operator', 'citizen')
def get_evacuation_route(request):
    lat = float(request.GET.get('lat'))
    lon = float(request.GET.get('lon'))
    validate_gps(lat, lon)

    routes = EvacuationRoute.objects.filter(active=True).order_by('estimated_time_min')[:3]
    return JsonResponse({'routes': list(routes.values())})
```

Figure 11 : Code corrigé utilisant des requêtes paramétrées (Django ORM)

4. Sécurisation des Communications (HTTPS/TLS) :

- **Instalation de mkcert pour générer un certificat :**

```
PS C:\WINDOWS\system32> choco install mkcert
Chocolatey v2.4.0
Installing the following packages:
mkcert
By installing, you accept licenses for the packages.
Downloading package from source 'https://community.chocolatey.org/api/v2/'

mkcert v1.4.4 [Approved] - Possibly broken
mkcert package files install completed. Performing other installation steps.
 ShimGen has successfully created a shim for mkcert.exe
 The install of mkcert was successful.
  Deployed to 'C:\ProgramData\chocolatey\lib\mkcert'

Chocolatey installed 1/1 packages.
 See the log for details (C:\ProgramData\chocolatey\logs\chocolatey.log).
PS C:\WINDOWS\system32> mkcert -install
Created a new local CA
The local CA is now installed in the system trust store!
The local CA is now installed in Java's trust store!

PS C:\WINDOWS\system32> cd "C:\Users\hp\Desktop\S6_SITCN_ENSIASD\Bases de données\Projet\-Tsunami-Ready (2)\Architects"
PS C:\Users\hp\Desktop\S6_SITCN_ENSIASD\Bases de données\Projet\-Tsunami-Ready (2)\Architects> mkcert localhost 127.0.0.1 ::1

Created a new certificate valid for the following names
 - "localhost"
 - "127.0.0.1"
 - "::1"

The certificate is at "./localhost+2.pem" and the key at "./localhost+2-key.pem"

It will expire on 9 July 2028
```

Figure 12 : Installation de mkcert pour générer un certificat TLS local

- **Instalation de mkcert pour générer un certificat :**

```python
'use strict';

const path = require('path');
const fs = require('fs');
const https = require('https');
const WebSocket = require('ws');
const cors = require('cors');


require('dotenv').config({ path: path.join(__dirname, '..', '.env') });

const express = require('express');
const app = express();
app.use(express.static(path.join(__dirname, '..')));   // '..' remonte d'un niveau

// Chargez les certificats
const options = {
  key: fs.readFileSync(path.join(__dirname, 'localhost+1-key.pem')),
  cert: fs.readFileSync(path.join(__dirname, 'localhost+1.pem'))
};

const server = https.createServer(options, app);
const wss = new WebSocket.Server({ server, path: '/ws' });
```

Figure 13 : Configuration de Django pour forcer HTTPS

- **Génération du certificat et clé privée avec mkcert:**

```
Administrateur : Invite de commandes - node  server.js

C:\Users\hp\Desktop\S6_SITCN_ENSIASD\Bases de données\Projet\-Tsunami-Ready (22)\Augmenteds_team\membre2-alerts>node server.js
ENV PATH = C:\Users\hp\Desktop\S6_SITCN_ENSIASD\Bases de données\Projet\-Tsunami-Ready (22)\Augmenteds_team\.env
TWILIO SID = MISSING
TWILIO TOKEN = MISSING
TWILIO FROM = MISSING
☑ MySQL connecté → tsunami_ready

🚀 TsunamiReady Server — Port 3001
API : https://localhost:3001/api
WS  : wss://localhost:3001/ws

── Statut Sécurité ──────────────────
Certificat SSL : ACTIF (mkcert) ☑

── Comptes ──────────────────────────
admin@agadir.ma   / admin2024!
citizen@agadir.ma / citizen2024!
```

Figure 14 : Génération du certificat et clé privée avec mkcert

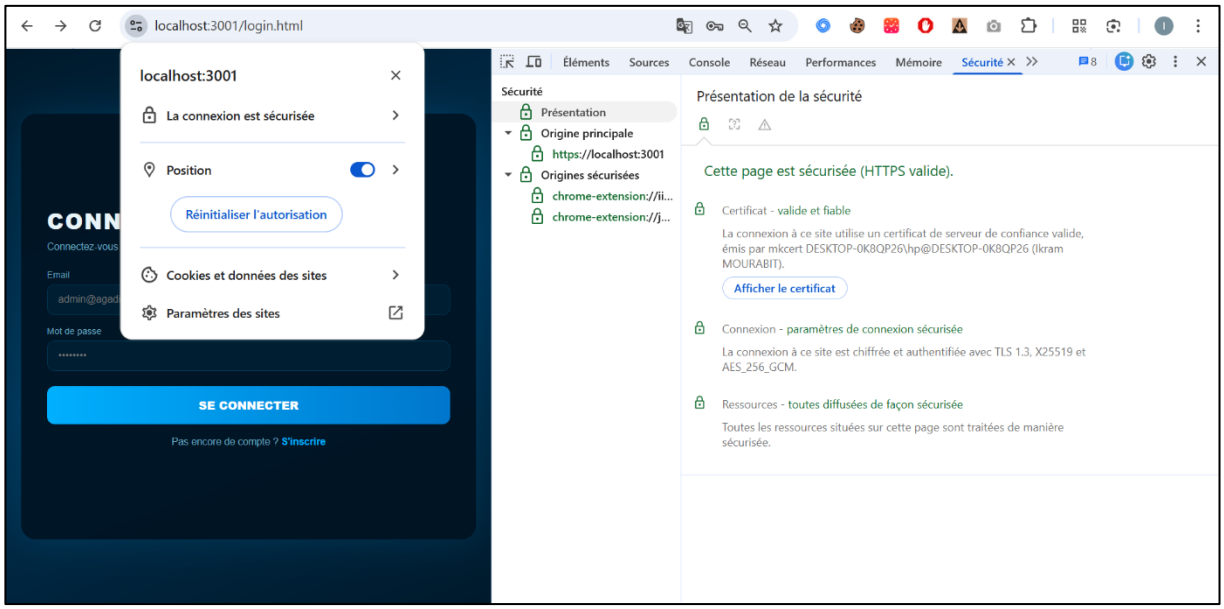

Figure 15 : Verification dans le navigateur

5. Signature HMAC des Signaux d'Alerte :

- **alertes/views.py**

➢ **Avant :**

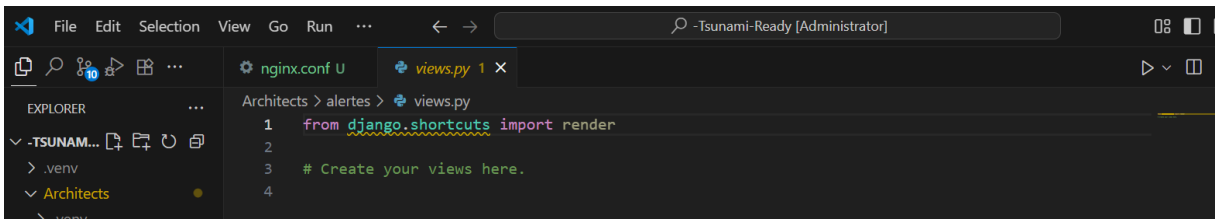

Figure 16 : Vue d'un capteur sismique avant signature HMAC

➢ **Après :**

```python
import hmac, hashlib, os
from django.http import JsonResponse
from django.views.decorators.http import require_POST
from utilisateurs.views import require_role

@require_POST
def receive_seismic(request):
    data = request.POST
    signature = request.headers.get('X-HMAC-Signature', '')

    if not verify_hmac(data, signature):
        return JsonResponse({'error': 'Signature invalide'}, status=403)

    magnitude = float(data.get('magnitude', 0))
    if not (0 <= magnitude <= 10):
        return JsonResponse({'error': 'Magnitude invalide'}, status=400)

def verify_hmac(data, received_sig):
    secret = os.environ['SEISMIC_HMAC_SECRET'].encode()
    payload = f"{data['magnitude']}{data['latitude']}{data['longitude']}{data['timestamp']}"
    expected = hmac.new(secret, payload.encode(), hashlib.sha256).hexdigest()
    return hmac.compare_digest(received_sig, expected)
```

Figure 17 : Vue sécurisée avec vérification de signature HMAC et timestamp

6. Trigger SQL – Déclenchement Sécurisé des Sirènes :

- **Fichier à créer/modifier : sql/security_setup.sql**

```sql
CREATE OR REPLACE FUNCTION trigger_tsunami_alert()
RETURNS TRIGGER AS $$
DECLARE
    v_alert_id INT;
    v_zones_affected INT;
BEGIN
    IF NEW.magnitude < 0 OR NEW.magnitude > 10 THEN
        RAISE EXCEPTION 'Magnitude invalide: %. Événement ignoré.', NEW.magnitude;
    END IF;

    IF NEW.latitude < 29.0 OR NEW.latitude > 31.5
       OR NEW.longitude < -10.0 OR NEW.longitude > -7.5 THEN
        RAISE EXCEPTION 'Coordonnées hors zone Souss-Massa. Événement ignoré.';
    END IF;

    IF NEW.magnitude >= 6.5 THEN
        UPDATE siren_zones
        SET status = 'ACTIVE', activated_at = NOW(), triggered_by_event = NEW.id
        WHERE coastal = TRUE AND status = 'STANDBY';

        GET DIAGNOSTICS v_zones_affected = ROW_COUNT;
```

Figure 18 : Trigger SQL pour déclenchement sécurisé des sirènes (partie 1)

```sql
        INSERT INTO tsunami_alerts (
            seismic_event_id, magnitude, alert_level, zones_activated,
            triggered_at, response_time_ms
        ) VALUES (
            NEW.id, NEW.magnitude, 'CRITICAL', v_zones_affected,
            NOW(), EXTRACT(MILLISECONDS FROM (NOW() - NEW.detected_at))
        ) RETURNING id INTO v_alert_id;

        RAISE NOTICE 'ALERTE TSUNAMI DÉCLENCHÉE - Magnitude: %, Zones: %, Alert ID: %'
            NEW.magnitude, v_zones_affected, v_alert_id;
    END IF;

    RETURN NEW;
END;
$$ LANGUAGE plpgsql SECURITY DEFINER;

CREATE TRIGGER check_tsunami_threshold
    AFTER INSERT ON seismic_events
    FOR EACH ROW
    EXECUTE FUNCTION trigger_tsunami_alert();
```

Figure 19 : Trigger SQL – validation des magnitudes et limites (partie 2)

7. Protection Firewall (UFW)

- **Fichier à créer : ufw_setup.sh**

```bash
#!/bin/bash

ufw default deny incoming
ufw default allow outgoing

ufw allow from 192.168.100.0/24 to any port 22
ufw allow 443/tcp
ufw allow from 10.0.0.0/8 to any port 5432
ufw allow from 10.0.0.0/8 to any port 3000

ufw limit ssh
ufw enable
```

Figure 20 : Script de configuration du firewall UFW

IV. Chiffrement des Données Sensibles :

1. Chiffrement au niveau base de données :

Le chiffrement des données sensibles dans le système *Agadir Tsunami-Ready* a été mis en place directement au niveau des modèles Django afin de garantir la confidentialité des informations critiques.

Les données sensibles, telles que les **coordonnées GPS des citoyens**, sont désormais chiffrées à l'aide de l'algorithme **AES-256** grâce à la bibliothèque django-encrypted-model-fields. Ce mécanisme permet d'assurer que les données ne sont **jamais stockées en clair dans la base de données**, même en cas de compromission.

- **Fichier modifié : utilisateurs/models.py**

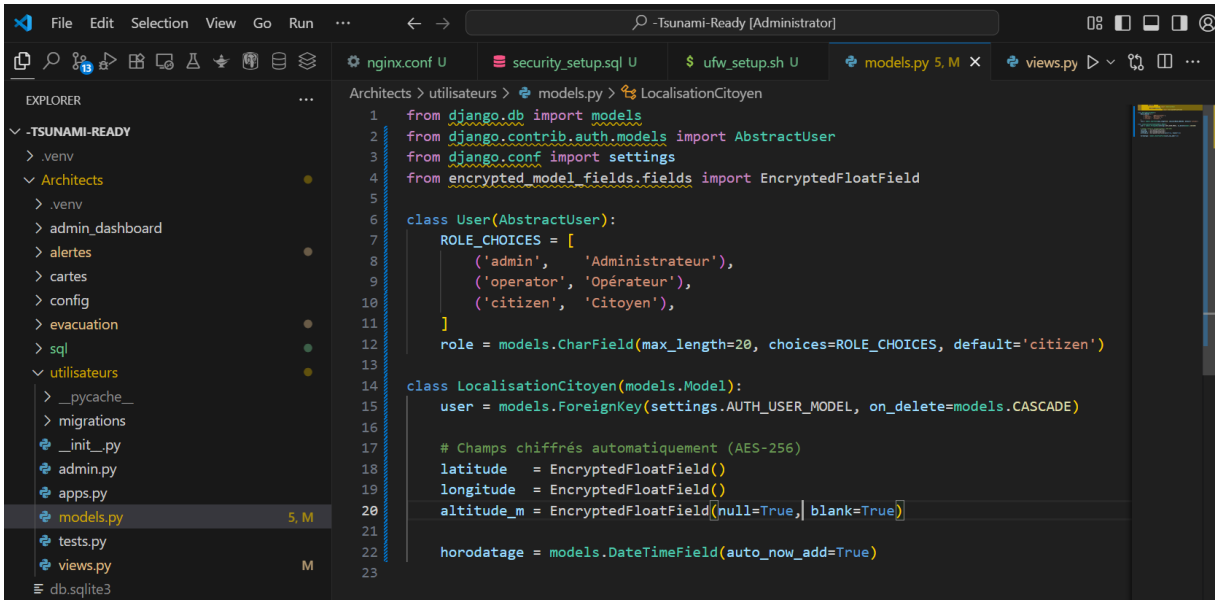

Figure 21 : Chiffrement AES-256 des coordonnées GPS dans le modèle Citizen

2. Variables d'environnement (gestion des secrets) :

Afin d'éviter toute exposition des informations sensibles, les clés et mots de passe ont été externalisés hors du code source.

Dans la version initiale, les informations sensibles étaient **directement codées dans les fichiers de configuration**, notamment dans settings.py. Cette pratique est fortement déconseillée, car elle expose les secrets en cas de partage du code ou de compromission du dépôt.

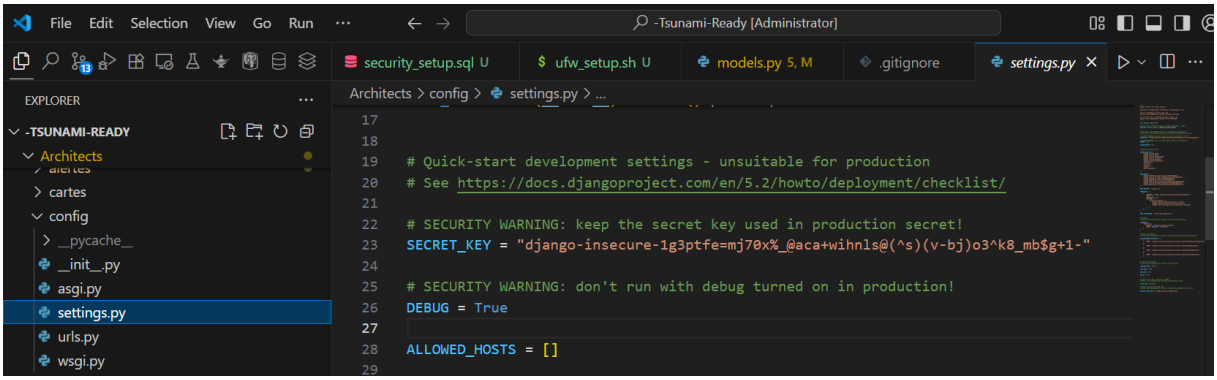

Figure 22 : Fichier setting

Pour corriger cette vulnérabilité, toutes les données sensibles ont été **externalisées dans un fichier sécurisé .env**, situé à la racine du projet. Ce fichier n'est pas versionné et reste accessible uniquement sur le serveur ou l'environnement local.

- **Fichier créé : .env**

Ce fichier contient l'ensemble des variables d'environnement nécessaires au fonctionnement de l'application.

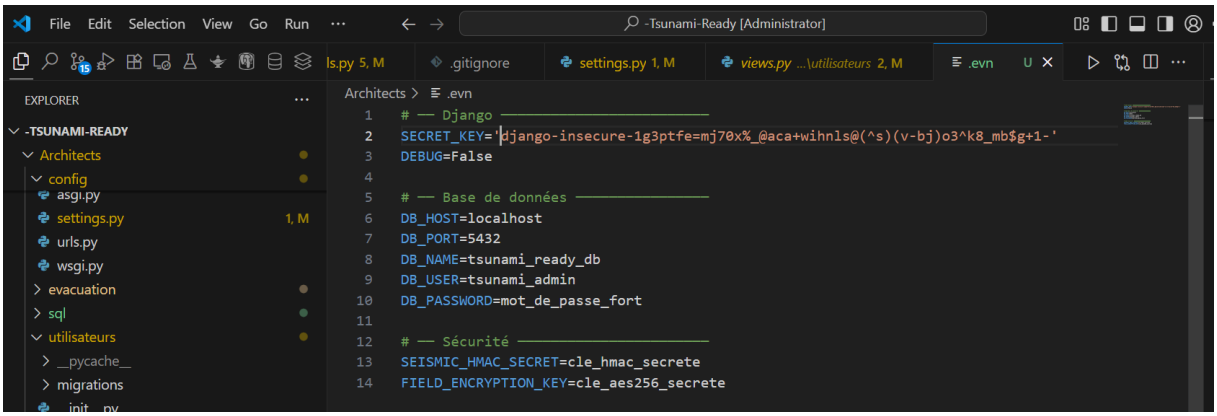

Figure 23 : Fichier .env contenant les secrets

- **Après :**

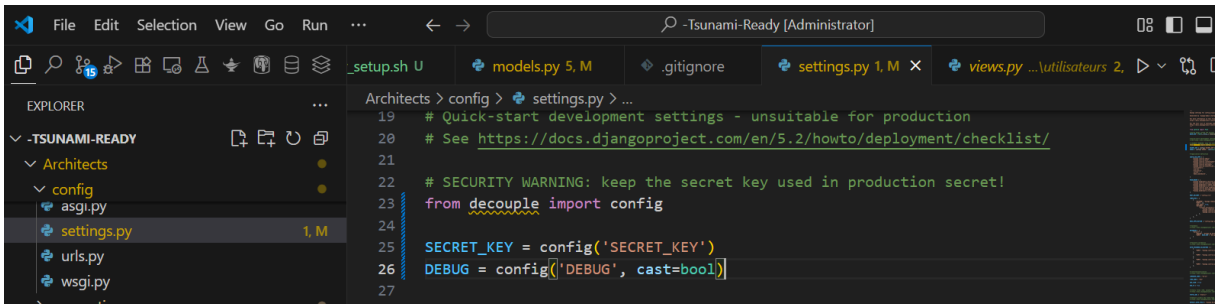

Figure 24 : settings.py final chargeant les variables depuis .env

Conclusion

En conclusion, ce projet de sécurisation du système **Agadir Tsunami-Ready** a permis de transformer une plateforme de gestion d'urgence en une infrastructure numérique résiliente et de confiance. Au-delà de l'implémentation technique, ce travail nous a confrontés aux réalités de la Confiance Numérique : protéger les données sensibles tout en garantissant la disponibilité d'une alerte critique.

Grâce à l'audit réalisé, nous avons pu neutraliser des failles majeures comme les injections **SQL** et les risques d'interception de données (**MITM**) via le déploiement de protocoles **HTTPS**. L'intégration de **Twilio** pour les alertes WhatsApp et l'utilisation du chiffrement **AES-256** pour les coordonnées **GPS** des citoyens assurent désormais une chaîne d'information à la fois intègre et efficace.